ДЕРЖАВНА СЛУЖБА УКРАЇНИ З НАДЗВИЧАЙНИХ СИТУАЦІЙ

НАКАЗ
(з основної діяльності)

від _____ 20____ р. Київ № _____

Про затвердження Методичних рекомендацій із складання, корегування та відпрацювання оперативних карток гасіння пожеж

Відповідно до підпункту 9 Положення про Державну службу України з надзвичайних ситуацій, затвердженого постановою Кабінету Міністрів України від 16 грудня 2015 р. № 1052 (зі змінами), з метою реалізації пункту 4 глави 3 розділу II Статуту дій органів управління та підрозділів Оперативно-рятувальної служби цивільного захисту під час гасіння пожеж, затвердженого наказом МВС від 26.04.2018 № 340 (зі змінами), зареєстрованим у Міністерстві юстиції України 10 липня 2018 року за № 802/32254, а також забезпечення керівника гасіння пожежі інформацією з питань організації оперативних дій під час її гасіння

НАКАЗУЮ:

1. Затвердити Методичні рекомендації із складання, корегування та відпрацювання оперативних карток гасіння пожеж (далі – Методичні рекомендації), що додаються.

2. Керівникам головних управлінь ДСНС України в областях та м. Києві, аварійно-рятувальних формувань центрального підпорядкування, закладів освіти системи ДСНС:

провести додаткові заняття з особовим складом щодо вивчення Методичних рекомендацій;

запровадити у службову діяльність та забезпечити неухильне дотримання вимог Методичних рекомендацій під час складання, корегування та відпрацювання оперативних карток гасіння пожеж.

3. Керівникам головних управлінь ДСНС України в областях та м. Києві, аварійно-рятувальних формувань центрального підпорядкування, Управління забезпечення цивільного захисту в органах державної влади ДСНС України забезпечити поетапне приведення оперативних карток гасіння пожеж у відповідність до Методичних рекомендацій:

протягом року з моменту видання наказу – на об’єкти та села в районах виїзду підрозділів;

протягом місяця з моменту видання наказу – на об’єкти критичної інфраструктури.

СЕД АСКОД **ДСНС України**
№ НС-1212 від 30.09.2025
Підписувач Даник Андрій Миколайович
Сертифікат 368DC35ECECB2DC10400000015A301006CF70400
Дійсний з 01.07.2024 0:00:00 по 30.06.2026 23:59:59

4. Визнати таким, що втратив чинність, наказ ДСНС від 24.10.2023 № 848 «Про затвердження Методичних рекомендацій із складання, корегування та відпрацювання оперативних карток гасіння пожеж».

5. Контроль за виконанням цього наказу покласти на першого заступника Голови ДСНС Миронюка В. Г.

Голова Андрій ДАНИК

ЗАТВЕРДЖЕНО
Наказ ДСНС
30.09.2025 № 1212

МЕТОДИЧНІ РЕКОМЕНДАЦІЇ
із складання, корегування та відпрацювання оперативних карток гасіння пожеж

I. Загальні положення

1. Ці Методичні рекомендації визначають загальний порядок складання, корегування та відпрацювання в органах та підрозділах ДСНС оперативних карток гасіння пожеж (далі – ОК).

2. ОК призначена для забезпечення керівника гасіння пожежі (далі – КГП) та штабу на пожежі довідковою інформацією з питань організації оперативних дій під час гасіння пожежі, яка в залежності від оперативної обстановки може змінюватись, а також для використання в підготовці осіб рядового та начальницького складу служби цивільного захисту в системі службової підготовки.

Перелік об'єктів, на які складаються оперативні картки (далі – Перелік), наведено в додатку 1 до цих Методичних рекомендацій.

3. Складання та корегування ОК доручається особовому складу органів управління та пожежно-рятувальних підрозділів, аварійно-рятувальних формувань (підрозділів) центрального підпорядкування (що мають свій район виїзду (об’єкти обслуговування) для реагування на пожежі, надзвичайні ситуації та інші небезпечні події).

ОК складаються у форматі (*.doc), (*.docx), (*.rtf) та (*.ods).

Контроль за своєчасним оновленням ОК покладається на керівників підрозділів.

4. Усі ОК вносяться в систему управління силами та засобами цивільного захисту (далі – СУСЗЦЗ), у тому числі у планшети КГП (за винятком об’єктів з обмеженим доступом).

5. Облік існуючих ОК ведеться:

в ОКЦ – усіх складених ОК в гарнізоні;

в пожежно-рятувальних підрозділах та аварійно-рятувальних формуваннях (підрозділах) центрального підпорядкування – ОК на об’єкти та села, розташовані в районах виїзду (обслуговування) відповідних підрозділів.

Організація заходів з обліку, складання, корегування та відпрацювання ОК покладається на старших помічників (помічників) начальників змін (з питань оперативного реагування) чергових змін оперативно-координаційних центрів (четверта зміна) та на начальників караулів (змін, відділень) або командирів відділень, де у штаті відсутні начальники караулів) підрозділів (четвертий караул (зміна)).

6. ОК на об’єкти знімаються з обліку в разі:

припинення діяльності (ліквідації) суб’єкта господарювання, який експлуатує об’єкт;

руйнування (знищення) об’єкта;

зміни функціонального призначення об’єкта.

7. ОК зберігаються в паперовому вигляді в підрозділах, а також в електронному вигляді в СУСЗЦЗ і у планшетах КГП.

ОК на об’єкти з обмеженим доступом зберігаються відповідно до встановлених чинним законодавством вимог.

На військові об’єкти та об’єкти критичної інфраструктури допускається внесення відкритої інформації, у тому числі в’їзди – виїзди з території, розташування джерел водопостачання та місць відключення електрики тощо.

8. До об’єктів фонду захисних споруд цивільного захисту / засобів колективного захисту (далі – укриття) належать:

захисні споруди цивільного захисту (сховища, протирадіаційні укриття), споруди подвійного призначення та найпростіші укриття, які є об’єктами нерухомого майна або утворюються в їх складі;

первинні (мобільні) укриття, які не є об’єктами нерухомого майна (розміщуються на місцевості на поверхні землі) та місцезнаходження яких може змінюватися в залежності від рішення балансоутримувача.

II. Складання оперативних карток гасіння пожеж

1. Отримання даних для складання та корегування ОК здійснюється на підставі пункту 59 частини другої статті 17-1, пунктів 4-5 частини п’ятої статті 24 Кодексу цивільного захисту України, пункту 2 частини шостої Положення про Державну службу України з надзвичайних ситуацій, затвердженого постановою Кабінету Міністрів України від 16 грудня 2015 р. № 1052, шляхом направлення органами управління та пожежно-рятувальними підрозділами відповідних інформаційних запитів до адміністрації об’єктів господарювання (власників, балансоутримувачів).

Крім того, можуть використовуватися дані з Єдиної державної електронної системи у сфері будівництва, доступ до якої може здійснюватися згідно з порядком, затвердженим постановою Кабінету Міністрів України від 23 червня 2021 р. № 681 «Деякі питання забезпечення функціонування Єдиної державної електронної системи у сфері будівництва», через електронний кабінет посадової особи територіального органу ДСНС.

Для своєчасного виявлення об’єктів, визначених Переліком, які були прийняті в експлуатацію, припинили свою роботу (були ліквідовані) або перестали підпадати під Перелік у зв’язку із зміною функціонального призначення, начальники районних управлінь територіальних органів ДСНС щорічно в IV кварталі організовують проведення звірки даних про такі об’єкти з місцевими органами влади та органами місцевого самоврядування. За результатами звірки до 10 числа місяця, наступного за звітним кварталом, надають відповідну інформацію до ОКЦ територіальних органів ДСНС та ДПРЗ, в районах виїзду яких знаходяться такі об’єкти.

У разі виявлення нового прийнятого в експлуатацію об’єкта у відповідності до законодавства України ОК на цей об’єкт складається протягом 1 місяця.

Розроблені ОК:

погоджуються підписом (печаткою) представника об’єкта (ОК на об’єкти) та керівником територіальної громади (ОК на села) на зворотній стороні кожного аркуша ОК;

у 15-денний термін вносяться до СУСЗЦЗ;

відпрацьовуються (практично) з особовим складом усіх караулів (змін, відділень).

2. У разі повідомлення про пожежу на об’єкті (в населеному пункті), на який складено ОК, підрозділ слідує до місця пожежі з ОК в паперовому вигляді (ОК може не братися у випадку наявності у начальника караулу (зміни, відділення) електронного планшета КГП).

3. Проведення розрахунків необхідної кількості техніки, яка автоматично направляється на об'єкт згідно зі встановленим рангом (номером) виклику, здійснюється відповідно до методики розрахунку сил та засобів Довідника керівника гасіння пожежі за найбільш складним варіантом розвитку пожежі.

Під час визначення рангу (номера) виклику на організації, установи і заклади з перебуванням людей у денний та нічний час враховувати максимальну кількість людей, які можуть перебувати у нічний час на об’єкті.

4. В залежності від номера (рангу) автоматичного направлення сил і засобів для гасіння пожежі ОК підписуються електронним цифровим підписом у системі електронного документообігу (АСКОД), зокрема:

1, 2 номер (ранг), а також ОК на села – начальниками пожежно-рятувальних підрозділів;

3 номер (ранг) – начальниками ДПРЗ;

4, 5 номер (ранг) – заступником начальника територіального органу ДСНС за напрямом реагування на надзвичайні ситуації.

5. ОК на об'єкт (додаток 2) складається з текстової і графічної частин.

5.1. Текстова частина має містити таку інформацію:

назва, відомча належність об’єкта, адреса;

основні контактні номери телефонів об’єкта;

кількість людей у денний та нічний час на об'єкті;

кількість пожежної техніки та членів ДПД на об'єкті;

ранг (номер) виклику, які підрозділи залучаються до гасіння відповідно до затвердженого Плану залучення сил та засобів цивільного захисту;

освітлення та газопостачання на об'єкті, місце розміщення головного електричного щита та місце відключення;

поверховість основних будівель і споруд, їх розміри у плані, ступінь вогнестійкості, перекриття та покрівлі, кількість сходових клітин і ліфтів, їх розташування та наявність захисту від задимлення;

конструктивні, планувальні і технологічні особливості, які можуть вплинути на швидке розповсюдження пожежі. За необхідності можуть наводитися розрізи окремих частин будівель, щоб показати порожнини в горючих будівельних

конструкціях, горючі підвісні стелі, горюче оздоблення стін на шляхах евакуації тощо;

наявність на об'єкті пожежо-, вибухонебезпечних, радіоактивних, отруйних, хімічних речовин і матеріалів, у тому числі таких, що вступають в реакцію з водою, та їх коротка характеристика небезпеки;

наявність, місткість та місцезнаходження об’єктів фонду захисних споруд цивільного захисту (далі – укриття) за умови їх розміщення у межах пішохідної доступності від меж об’єкта (до 300 м для багатоповерхової, підвищеної та висотної забудови і об’єктів, віднесених до категорій цивільного захисту, та до 500 м для середньоповерхової й малоповерхової забудови);

короткі рекомендації КГП до гасіння пожежі або ліквідації наслідків НС відповідно до аварійних карток у разі наявності на об’єкті небезпечних речовин;

наявність систем пожежогасіння та розташування їх вузлів управління;

наявність внутрішнього та зовнішнього протипожежного водопостачання, зокрема кількість пожежних гідрантів, тип та діаметр мережі, місце включення насосів-підвищувачів, кількість пожежних водойм та пірсів, водонапірних веж та градирень, місця їх розміщення, об'єм, спосіб забору води з них, а також наявність вододжерел поблизу об'єкта, які можливо використати для пожежогасіння.

Додатково в ОК на об’єктах:

паливно-енергетичного сектору додатково необхідно вказати тип і розмір резервуарів (ємностей), вид нафтопродуктів, які в них зберігаються, наявність обвалування резервуарів, під'їзних шляхів до них, кількість і місця зберігання піноутворювача на об’єкті, тип силового обладнання, кількість мастила, наявність та кількість приладів заземлення;

закладів охорони здоров’я із стаціонаром, закладів освіти з нічним перебуванням неповнолітніх дітей, будинків-інтернатів (у тому числі для громадян похилого віку та осіб з інвалідністю) та санаторіїв (далі – об’єкти з нічним перебуванням) у Картці обліку перебування людей у нічний час (додаток 3) ведеться облік наявної чисельності людей у нічний час. Ця картка заводиться на поточний місяць і заповнюється оператором базового пожежно-рятувального підрозділу або черговим по караулу (в підрозділах, де не організовано чергування оператора) до 22 години поточної доби;

критичної інфраструктури вказуються місця підключення автономного електроживлення;

зв’язку, критичної інфраструктури з наявністю серверних кімнат, центрів обробки даних з інформаційно-технологічною інфраструктурою відображуються місця розташування приміщень центрів обробки даних і серверних, кабельних лотків, а також рекомендації КГП щодо гасіння пожеж з урахуванням особливостей приміщень та обладнання.

5.2. Графічна частина ОК має включати план території об'єкта та поверхові плани основних будівель і споруд (включаючи підвали та технічні поверхи). Для складання плану території використовувати графічні редактори або використання Google-карт з нанесенням на неї установлених у системі ДСНС умовних графічних позначень та знаків.

На плані території об’єкта умовними позначками слід наносити:

основні будівлі, споруди та відкриті технологічні установки;

дороги, проїзди та залізничні колії на території об'єкта;

розташування головного електричного щита, газорозподільчої підстанції;

місця проходження трубопроводів з горючими рідинами та газами;

розміщення джерел протипожежного водопостачання із зазначенням основних їх характеристик. Зазначити відстань до найближчих джерел протипожежного водопостачання, розташованих на прилеглій до об’єкта території;

місця розташування та підключення резервних джерел електроживлення;

місця розташування сонячних панелей та місця їх відключення;

наявність, місткість та місцезнаходження укриттів (за умови їх розташування в радіусі пішохідної доступності) із позначенням місцезнаходження входу до таких об’єктів;

під’їзні шляхи до об’єкта та місця в’їзду на його територію.

При складанні поверхових планів основних будівель і споруд дозволяється використовувати графічні редактори, схеми з проектної документації на об’єкт та (або) плани, створені в бюро технічної інвентаризації з використанням систем автоматизованого проектування.

На поверхових планах основних будівель і споруд необхідно зазначити:

сходові клітини і ліфти, виходи на горище, на колосники та входи в підвал тощо;

місця розташування електричних щитів і внутрішніх пожежних кранів;

приміщення, де знаходяться вузли управління системами пожежогасіння, димовидалення, аварійної, припливної та витяжної вентиляції, опускання протипожежної завіси, аварійного зливання горючих рідин тощо;

серверні кімнати та приміщення, де розташовані центри обробки даних з інформаційно-технологічною інфраструктурою.

Для сигнального маркування ОК на першій сторінці по діагоналі зліва направо від низу до верху наноситься смуга шириною 10–15 мм відповідним кольором, зокрема:

жовтий – небезпечна речовина (хімічна, отруйна, вибухова, радіоактивна тощо);

червоний – об'єкти з цілодобовим перебуванням людей.

Кольоровим фоном, що відповідає кольору маркувальної полоси на першій сторінці, у графічній частині ОК (поверхових планах та схемах територій) необхідно позначити будівлі і приміщення, де в нічний час перебувають люди та у яких знаходяться небезпечні речовини і матеріали.

5.3. У текстовій частині ОК на село (додаток 4) вказується:

чисельність населення;

наявність та розташування джерел протипожежного водопостачання (пожежні гідранти, водонапірні вежі, водойми, пірси);

джерела протипожежного водопостачання, які не вказані на схемі або розташовані поблизу населеного пункту (в сусідніх населених пунктах);

сили та засоби, що залучаються на гасіння пожежі;

відстань та маршрут слідування найближчого пожежно-рятувального підрозділу ДСНС.

5.4. У графічній частині ОК на село необхідно позначити розташування:

адміністративних будинків, шкіл, дитячих садків, клубів, лікарень, поліклінік, виробничих та складських будівель, трас магістральних газо- та продуктопроводів, об’єктів, де знаходяться небезпечні хімічні, отруйні, радіоактивні, вибухонебезпечні, горючі та легкозаймисті речовини;

електротрансформаторних та газорозподільчих підстанцій;

джерел протипожежного водопостачання (пожежні гідранти, водонапірні вежі, водойми, пірси) та їх характеристику;

наявність та місце розташування об’єктів фонду захисних споруд із зазначенням максимально можливої кількості осіб, які можуть у них перебувати, місць входу до них;

укриттів (наявність, місткість та місцезнаходження);

доріг, по яких прибуває найближчий пожежно-рятувальний підрозділ, та напрямків до сусідніх населених пунктів.

5.5. Під час складання графічної частини ОК використовуються умовні позначення, визначені додатком 4 Статуту дій органів управління та підрозділів Оперативно-рятувальної служби цивільного захисту під час гасіння пожеж, затвердженого наказом МВС від 26.04.2018 № 340, зареєстрованим у Міністерстві юстиції України 10 липня 2018 року за № 802/32254, а також умовні позначення та знаки, визначені додатком 5 до цих Методичних рекомендацій.

6. Відомості про укриття мають відповідати інформаційно-комунікаційній системі «Інформаційна система «Облік та візуалізація фонду захисних споруд цивільного захисту» станом на дату складання ОК.

III. Корегування оперативних карток гасіння пожеж

1. Корегування ОК на об'єкти та села здійснюється один раз на 5 років відповідно до Плану-графіка корегування ОК (далі – План-графік), який складається на календарний рік (додаток 6).

План-графік корегування ОК на об'єкти розробляється начальниками пожежно-рятувальних підрозділів (аварійно-рятувальних формувань (підрозділів) центрального підпорядкування (що мають свій район виїзду (об’єкти обслуговування)) та затверджується начальником пожежно-рятувального загону, до якого входить цей підрозділ, а в аварійно-рятувальних формуваннях центрального підпорядкування – їх керівниками. Згідно із планами-графіками підрозділів на ОКЦ формується виписка щодо корегування ОК на об’єкти за 4 та 5 номером (рангом).

2. Крім планового корегування ОК на об'єкти та села один раз на 5 років, корегування здійснюється у дванадцятиденний термін після виявлення недоліків під час гасіння пожежі та після проведення практичного відпрацювання ОК.

3. Контроль за корегуванням ОК здійснюється:

за номерами (рангами) 1, 2, 3, а також ОК на села – начальником ДПРЗ;

за номерами (рангами) 4, 5 – заступником начальника центру (з питань оперативного реагування) ОКЦ.

4. Під час корегування паперовий варіант ОК з ПЗЧ не вилучається.

5. Після здійснення корегування ОК робиться відповідна відмітка в аркуші корегування та відпрацювання ОК.

6. Копії ОК на села в зоні обслуговування повинні знаходитися в офіцера-рятувальника громади. У разі виявлення змін офіцером-рятувальником громади надається відповідна інформація до пожежно-рятувального підрозділу, в районі виїзду якого знаходиться населений пункт, з метою корегування ОК.

7. Інформація про укриття, зазначена в ОК, підлягає корегуванню лише у випадках, визначених пунктами 1, 2 цього розділу.

IV. Відпрацювання оперативних карток гасіння пожеж

1. Практичне відпрацювання ОК на об’єктах здійснюється з усіма караулами (змінами):

щорічно – на об’єктах за рангами 4-5;

один раз на 3 роки – на об’єктах за рангом 3;

один раз на 5 років – на об’єктах за рангами 1-2.

Під час практичного відпрацювання додатково здійснюється перевірка джерел зовнішнього протипожежного водопостачання, що можуть використовуватися для гасіння пожежі.

2. Теоретичне відпрацювання всіх ОК здійснюється після складання або корегування у 12-денний термін.

3. Практичне та теоретичне відпрацювання ОК не проводиться у разі, якщо до настання визначеного планом-графіком терміну проводилося гасіння пожежі.

4. Організація відпрацювання ОК на об’єкти в районі виїзду пожежно-рятувального підрозділу, в тому числі погодження з адміністрацією об’єктів порядку допуску на їх територію особового складу і техніки, покладається на начальника цього підрозділу.

5. Відпрацювання ОК на об'єкти здійснюється відповідно до Плану-графіка відпрацювання ОК, який розробляється (1 раз на 5 років) та підписується начальником підрозділу (додаток 7).

6. За окремим рішенням ДСНС або його територіального органу додатково може проводитись відпрацювання ОК.

7. Після здійснення відпрацювання ОК робиться відповідна відмітка в аркуші корегування та відпрацювання ОК.

Директор Департаменту реагування
на надзвичайні ситуації Володимир КАЧКАН

Додаток 1
до Методичних рекомендацій із складання, корегування та відпрацювання оперативних карток гасіння пожеж
(пункт 2 розділу I)

ПЕРЕЛІК
об'єктів, на які повинні складатися оперативні картки гасіння пожеж

1. Об'єкти електроенергетики:

атомні і теплові електростанції, теплоелектроцентралі незалежно від потужності;

стаціонарні дизельні і газотурбінні, сонячні, вітрові електростанції та гідроелектростанції потужністю від 20 мВт;

електричні підстанції напругою від 330 кВ.

2. Об’єкти транспортної інфраструктури:

вокзали залізничного, річкового, морського, автомобільного і повітряного транспорту з пропускною спроможністю від 2 000 тис. осіб на добу;

наземні споруди та підземні станції метрополітену;

аеропорти із злітно-посадковою смугою 6 та вищої категорії;

морські та річкові порти і термінали;

автотранспортні підприємства, тролейбусні і трамвайні парки;

багатоповерхові наземні та підземні стоянки (гаражі) від 100 паркомісць.

3. Промислові підприємства або окремо розташовані технологічні установки:

об’єкти з видобутку і підготовки нафти, газу або газоконденсату;

нафто-, газопереробні підприємства, виробництво зріджених горючих вуглеводнів;

хімічні та нафтохімічні підприємства;

коксохімічні підприємства;

підприємства титано-магнієвого виробництва;

підприємства з виробництва та переробки (утилізації) синтетичного каучуку, шин та інших гумотехнічних виробів;

виробництво мінеральних добрив, що мають вибухо-, пожежонебезпечні властивості;

деревообробні підприємства продуктивністю від 500 $м^3$ на добу;

целюлозно-паперове виробництво;

хлібокомбінати та хлібозаводи;

підприємства металургії та машинобудування;

підприємства текстильного і швейного виробництва з площею виробничих приміщень понад 1000 кв. м;

наземні споруди вугільних шахт.

4. Об’єкти, на яких виробляються, використовуються у технологічних процесах або зберігаються вибухові, небезпечні хімічні та радіоактивні речовини і матеріали.

5. Підприємства з вироблення і переробки сільськогосподарської продукції:

тваринницькі, птахівницькі ферми та комплекси площею у плані від 10 000 м^2;

елеватори та хлібоприймальні пункти місткістю від 2 000 тонн;

млини та комбікормові заводи продуктивністю 50 тонн на добу;

маслоекстракційні заводи.

6. Складські об’єкти:

склади нафти, нафтопродуктів, інших легкозаймистих і горючих рідин та горючих газів, у тому числі об’єктові, загальною місткістю від 5 000 м^3;

торгово-складські приміщення площею від 10 000 м^2;

промислові холодильники (з використанням аміаку).

7. Окремі будівлі та споруди:

адміністративно-офісні будівлі з умовною висотою від 15 м, від 4 поверхів або з чисельністю 300 і більше працюючих;

будівлі та споруди з металевих конструкцій і горючим утеплювачем площею від 10 000 м^2.

8. Заклади охорони здоров'я:

лікарні із цілодобовим стаціонаром;

реабілітаційні центри, лікувально-профілактичні та оздоровчі заклади з цілодобовим стаціонаром;

амбулаторно-поліклінічні заклади (3 поверхи та вище або які розташовані на 3 поверсі та вище).

9. Заклади соціального забезпечення:

будинки для людей похилого віку та людей з обмеженими можливостями із цілодобовим стаціонаром;

заклади соціального забезпечення з цілодобовим або нічним перебуванням людей.

10. Навчальні та дошкільні заклади:

дитячі сади (комбінати) на 100 місць і більше;

школи-інтернати;

загальноосвітні школи і навчальні заклади на 150 і більше студентів або учнів;

літні спортивні та оздоровчі табори і дитячі дачі на 100 місць і більше.

11. Громадські та адміністративні будинки і споруди:

адміністративні будівлі органів державної влади, особливих центральних органів державного управління, органів місцевої влади та органів місцевого самоврядування (районного рівня та вище);

будівлі судових та правоохоронних органів (районного рівня та вище);

банківські установи з наявністю сховищ;

торгові центри, маркети, універмаги та криті ринки з площею поверху від 5 000 м^2;

готелі, гуртожитки та мотелі від 4 поверхів;

бази відпочинку, пансіонати.

12. Культурно-видовищні та розважальні заклади:

пам'ятки архітектури та історії, музеї, картинні галереї, виставкові комплекси та зали висотою 2 та більше поверхів;

бібліотеки, архіви з фондом зберігання більше 500 000 одиниць;

театри, філармонії, кіноконцертні зали, палаци та будинки культури, цирки та інші видовищно-розважальні заклади на 300 і більше глядачів;

розважальні заклади (казино, ресторани, клуби), у тому числі і нічні, розраховані на перебування 300 і більше людей;

заклади громадського харчування закритого типу (ресторани, кафе, клуби), розраховані на одночасне перебування від 100 відвідувачів;

апаратно-студійні комплекси телекомпаній;

лазні-сауни, розраховані на одночасне перебування від 100 відвідувачів.

13. Спортивні комплекси і споруди (стадіони, манежі), розраховані на 1000 і більше місць.

14. Культові будівлі та споруди площею від 1000 м^2, а також такі, що становлять культурно-історичну цінність.

15. На села.

На всі села в районі виїзду підрозділів.

16. Об’єкти критичної інфраструктури

На всі об’єкти критичної інфраструктури в районі виїзду підрозділів, які не увійшли до переліку об’єктів, визначених пунктами 1–14 цього додатка.

_____

Додаток 2
до Методичних рекомендацій із складання, корегування та відпрацювання оперативних карток гасіння пожеж
(пункт 5 розділу II)

Оперативна картка гасіння пожежі на об'єкті

<table>
<tr><td>Назва та відомча належність об'єкта:</td><td colspan="2"><u>ПрАТ “Київський завод безалкогольних напоїв “Росинка”, приватне акціонерне товариство</u></td><td>Ранг (номер) виклику:</td><td>3</td></tr>
<tr><td>Адреса об'єкта:</td><td colspan="2">м. Київ, вул. Ежена Потьє, 6</td><td colspan="2" rowspan="3">На пожежу виїжджають 17 од.: 8 АЦ, 1 АД-30, 1 КП, 2 АГДЗС, 2 САРМ.</td></tr>
<tr><td>Номери телефонів:</td><td colspan="2">456 41 31 – черговий (цілодобово)
456 70 44 – охорона (прохідна)
256 80 51 – відділ охорони праці</td></tr>
<tr><td>Кількість людей на об'єкті:
ніч <u>8 чол.</u>, день <u>525 чол.</u></td><td colspan="2">Кількість пожежної техніки та членів ДПД на об'єкті: 1 АЦ, 33 чол.</td></tr>
<tr><td colspan="5">Шляхи проїзду на територію об'єкта, кількість в'їздів: 1 заїзд з вул. Яблунева</td></tr>
<tr><td colspan="4">Електропостачання на об'єкті:</td><td>220/380В</td></tr>
<tr><td colspan="4">Газопостачання на об'єкті:</td><td>об'єкт газифіковано</td></tr>
<tr><td colspan="4">Опалення на об'єкті:</td><td>центральне водяне та індивідуальне газове (від котельні)</td></tr>
<tr><td colspan="2">Місце відключення електроенергії:</td><td colspan="3">Освітлювально-силову мережу напругою 220В може бути відключено особовим складом караулу від головних електрощитів, які розташовані на перших та підвальних поверхах будівель</td></tr>
<tr><td colspan="2">Місце перекриття газопостачання на території:</td><td colspan="3">Газова розподільча підстанція знаходиться на території об'єкту біля складу пустої тари (див. схему). Відключення здійснюється представником об’єкта або газової служби</td></tr>
<tr><td colspan="2">Наявність та розташування внутрішніх не задимлюваних сходових клітин</td><td colspan="3">відсутні</td></tr>
<tr><td>Характеристика об'єкта (будівель, приміщень):</td><td colspan="4"><u>Головний корпус (цех № 1, цех № 3)</u>
Будівля 4-поверхова, прямокутної форми, II ступеня вогнестійкості, розміром у плані 84 м Х 36 м, загальною площею – 12096 кв. м. Висота будівлі на рівні горищного перекриття 15 м.
Стіни та перегородки виконано із силікатної цегли. Оздоблення стін та стелі в коридорах та приміщеннях з 1-го по 4-й поверх з негорючих матеріалів (металевий сайдинг).
Перекриття між поверхами з 1-го по 4-й з багатопустотних залізобетонних плит.
Дах – руберoїдний по бітумній мастиці.
У будівлі п’ять внутрішніх сходових клітин та чотири ліфти (див. схему).

<u>Компресорний цех</u>
Будівля 1-поверхова, прямокутної форми, II ступеня вогнестійкості, розміром у плані 35 м Х 19 м, загальною площею – 665 кв. м. Висота будівлі на рівні горищного перекриття 5 м.
Стіни та перегородки виконано із силікатної цегли. Оздоблення стін та стелі в коридорах та приміщеннях з негорючих матеріалів (металевий сайдинг).</td></tr>
</table>

Продовження додатка 2

	Дах – рубероїдний по бітумній мастиці. **<u>Склад тари та сировини</u>** **Будівля** 2-поверхова, прямокутної форми, II ступеня вогнестійкості, розміром у плані 25 м Х 15 м, загальною площею – 750 кв. м. Будинок з підвальним поверхом, загальна площа підвалу – 150 кв. м. Висота будівлі на рівні горищного перекриття 10 м. **Стіни та перегородки** виконано із силікатної цегли. Оздоблення стін та стелі в коридорах та приміщеннях з 1-го по 2-й поверх з негорючих матеріалів (металевий сайдинг). **Перекриття** між поверхами з 1-го по 2-й з багатопустотних залізобетонних плит. **Дах** – рубероїдний по бітумній мастиці. **У будівлі одна внутрішня сходова клітина та один ліфт** (див. схему). **<u>Цех № 2</u>** **Будівля** 1-поверхова, прямокутної форми, II ступеня вогнестійкості, розміром у плані 35 м Х 25 м, загальною площею – 875 кв. м. Будинок з підвальним поверхом, загальна площа підвалу – 700 кв. м. Висота будівлі на рівні горищного перекриття – 5 м. **Стіни та перегородки** виконано із силікатної цегли. Оздоблення стін та стелі в коридорах та приміщеннях з негорючих матеріалів (металевий сайдинг). **Дах** – рубероїдний по бітумній мастиці. **У будівлі одна внутрішня сходова клітина** (див. схему).

Речовини і матеріали, що використовуються (зберігаються) на об'єкті, наявність:	
вибухонебезпечних речовин:	відсутні
радіоактивних речовин:	відсутні
хімічних рідин та речовин:	аміак, який використовується в компресорному цеху в закритому циклі – 1,8 тонни та у ресиверах, які розташовані на подвір'ї, – 1,4 тонни (див. схему)
рекомендації КГП до гасіння пожежі або ліквідації наслідків розливу відповідно до аварійних карток	Гасити пожежу з максимально можливої відстані, за якої забезпечується гасіння пожежі. Охолоджувати ємності водою, не допускати потрапляння води в ємності. Не припиняти гасіння, поки є витікання. Для розсіювання (осадження, ізоляції) парів використовувати розпилену воду. Розміри зони хімічного забруднення уточнюються за результатами хімрозвідки. Повідомити СЕС. У небезпечну зону входити лише в засобах індивідуального захисту. Триматися навітряного боку. Уникати низьких місць. Не торкатися пролитої речовини. Потерпілим надати першу допомогу. Задіяти відповідні служби для усунення витікання, перекачування аміаку у справну ємність, огородження місць розливів ґрунтовим валом, нейтралізації розливів. Проливання ізолювати піною. Не допускати потрапляння у водойми, підвали, каналізацію. Допускається змивання водою невеликих розливів рідкого аміаку за умов співвідношення кількості води та аміаку не менше 10:1, а також нейтралізація невеликих розливів аміаку вуглекислотою. Змивання та розбавлення водою великої кількості аміаку не дозволяється, тому що може спричинити збільшення концентрації аміаку в повітрі внаслідок випаровування аміаку під дією тепла, яке виділяється під час розчинення аміаку у воді. Для нейтралізації використовувати 1–10% розчини сірчаної, азотної, соляної кислот, а також воду. Норма витрат – 6–20 літрів на 1 літр аміаку.
речовин, що вступають в реакцію з водою:	відсутні

Продовження додатка 2

речовин, що застосовуються для охолодження обладнання	аміак (знаходиться у трубопроводах компресорного цеху) (див. схему)
Наявність автоматичної установки пожежогасіння (місце включення)	Компресорний цех та ресивери обладнані дренчерною системою водяного пожежогасіння, насосна станція розміщена у прибудові головного корпусу. Засувки дренчерної системи розташовані безпосередньо в компресорному цеху
Зовнішнє протипожежне водопостачання, кількість пожежних гідрантів, тип та діаметр мережі, водоймища, градирні, штучні та природні водойми:	**Вуличні ПГ:** 1. ПГ-44* вул. Яблунева, 6 (відстань 20 м) К-150; 2. ПГ-45* вул. Яблунева, 6 (відстань 10 м) К-150; 3. ПГ-46* вул. Яблунева, 6 (відстань 25 м) К-150; * номер вуличного ПГ відповідно до інвентаризаційної відомості **Об'єктові ПГ:** ПГ-1 (відстань 10 м) Т-150. На території об’єкта знаходиться пожежне водоймище на **200 м^3** та дві градирні (одна на **120 м^3** та одна на **90 м^3**), які розташовані біля гаража. Озеро на відстані 1200 м
Внутрішнє протипожежне водопостачання (місце включення)	Для забезпечення подачі води по коридорам будівель встановлено сухотруби Ø 51 мм зі з’єднувальними головками типу «Богданова»: головний корпус – 22 ПК; цех № 2 – 6 ПК; гараж – 3 ПК. Місце включення насосів-підвищувачів (насосна станція) – на 1 поверсі головного корпусу цеху № 1 та № 3
Місце розташування об’єктів фонду захисних споруд із зазначенням максимально можливої кількості осіб	1. Вул. Яблунева, 6 (відстань 100 м), місткість укриття – 120 чол. 2. Вул. Яблунева, 8 (відстань 200 м), місткість укриття – 40 чол. 3. Вул. Яблунева, 10 (відстань 300 м), місткість укриття – 50 чол.

Продовження додатка 2

ПЛАН підвалу та 1-го поверху
Адміністративної будівлі (вул. Яблунева, 6)

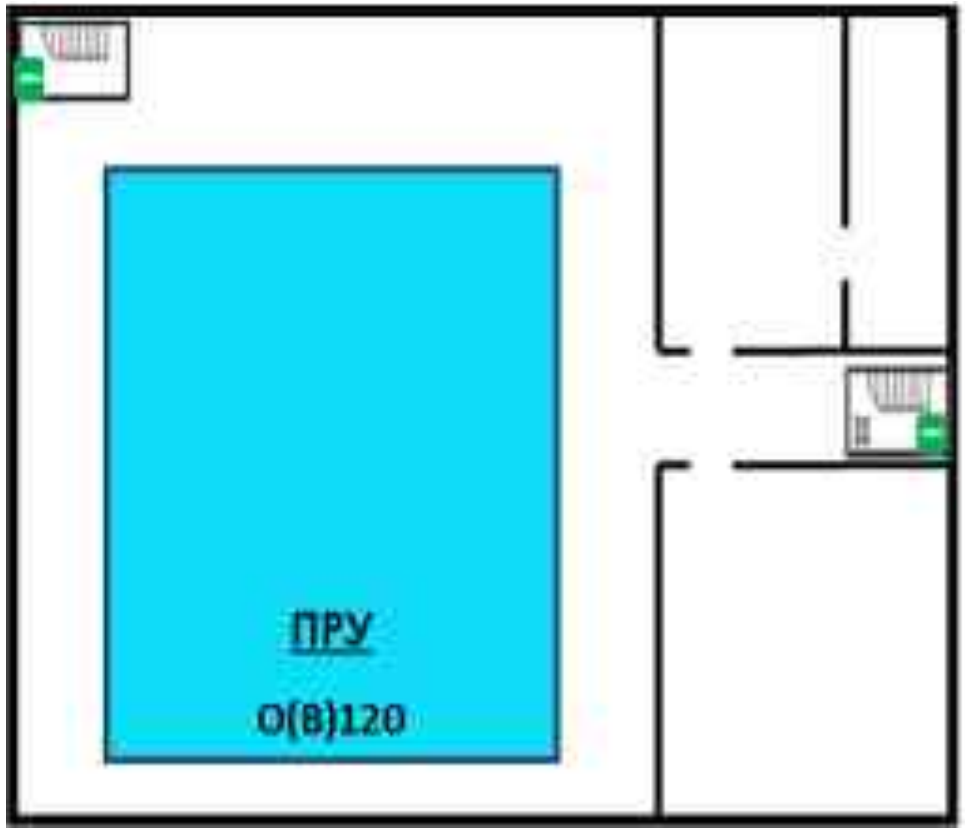

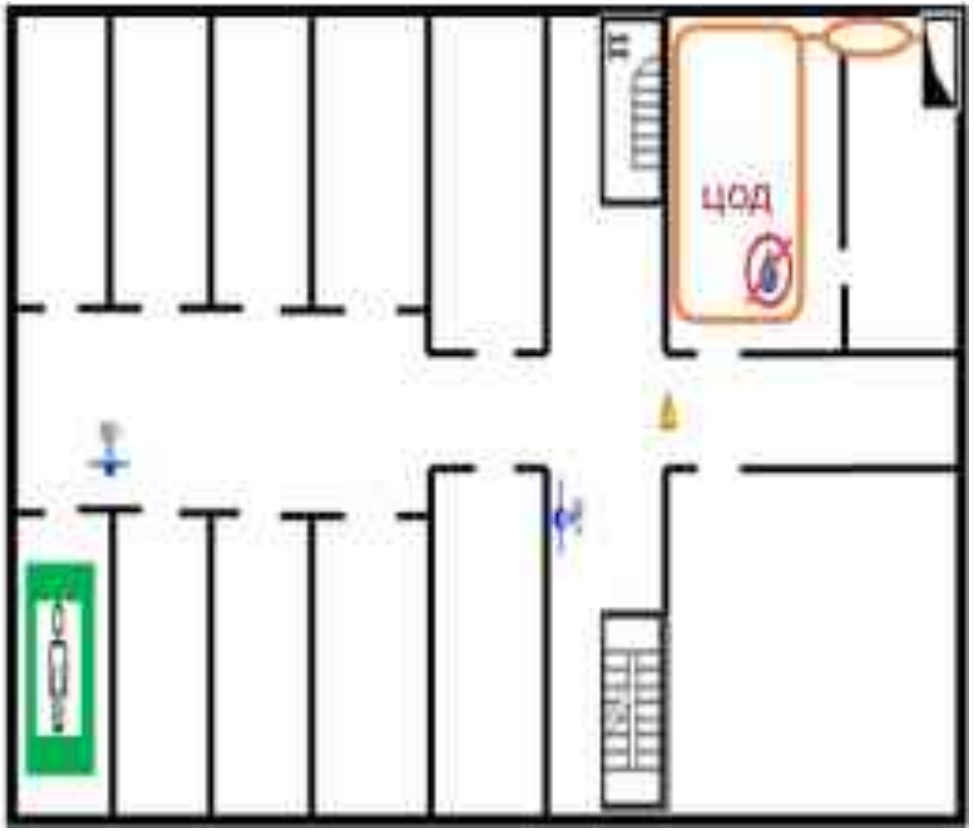

Продовження додатка 2

План території ПАТ Київський завод безалкогольних напоїв „Росинка"

1 - Головний корпус; 2 - Компресорний цех; 3 - Склад тари та сировини; 4 - Цех № 2; 5 - Гараж

Продовження додатка 2

Аркуш
корегування та відпрацювання оперативної картки

З яким караулом (зміною) вдіпрацьовано, ким відкореговано ОК (прізвище)			
1 караул (зміна)	2 караул (зміна)	3 караул (зміна)	4 караул (зміна)
1	2	3	4
	01.01.2025 Корегування ІВАНЕНКО		
02.01.2025 Відпрацьовано ПЕТРЕНКО	03.01.2025 Відпрацьовано БОБРИКА	04.01.2025 Відпрацьовано ЗАВІРЮХА	05.01.2025 Відпрацьовано КАПІТАНОВ
		01.01.2030 Коригування ЗАВІРЮХА	

Додаток 3
до Методичних рекомендацій із складання, корегування та відпрацювання оперативних карток гасіння пожеж
(пункт 5.1 розділу II)

КАРТКА ОБЛІКУ
перебування людей у нічний час

у _____
(найменування організації, установи, закладу з цілодобовим перебуванням людей)

за _____ 20___ року
(місяць)

Дата	Місцезнаходження (корпус, поверх, відділення тощо)	Кількість пацієнтів / персоналу	Примітки

_____

Додаток 4
до Методичних рекомендацій із складання, корегування та відпрацювання оперативних карток гасіння пожеж
(пункт 5.3 розділу II)

ЗРАЗОК

ЗАТВЕРДЖУЮ

_____

_____
(посада, спеціальне звання, власне Ім'я та ПРІЗВИЩЕ)

ОПЕРАТИВНА КАРТКА ГАСІННЯ ПОЖЕЖ
на село Власівка

Територіальна належність	Полтавський район
Територіальна громада	Зіньківська ТГ
Населення	850 чол.
Район виїзду пожежно-рятувального підрозділу ДСНС	15 ДПРЧ
Відстань до найближчогопожежно-рятувального підрозділуДСНС	7 км
Маршрут слідування	м. Зіньків – с. Власівка по трасі Р-34
Номери телефонів	РВ ГУ НП, тел. **12 34 22**
	Старостат, тел. **674 12 11** староста **Лютик Надія Іванівна (моб. 067 456 34 88)**

Джерела протипожежного водопостачання, не вказані на схемі	На відстані 4 км по залізничній колії в західному напрямку, на станції ПЛАТФОРМА 1178 розташована водонапірна вежа із запасом води 7 м. куб. На відстані 3 км в напрямку Полтави на 457 км траси знаходиться зрошувальний канал з необмеженим запасом води, встановлення ПА на два всмоктувальні рукави можливе біля насосної або з дамби

Сили та засоби, що залучаються на гасіння пожежі:

Номер виклику	Найменування МПО та інших протипожежних формувань	Вид техніки	Відстань, км
По першому виклику	**МПК-1 с. Власівка**	**АЦ-40**	**5 км**
	МПО-1 с. Дейкалівка	**АЦ-40**	**21 км**
По додатковому виклику	**15 ДПРЧ**	**АЦ-40**	**25 км**
	33 ДПРЧ	**АЦ-40**	**25 км**
	38 ДПРЧ	**АЦ-40**	**35 км**
Згідно із зоною обслуговування зведених загонів	Основна та спеціальна техніка АРЗ СП та підрозділів зони обслуговування 1-го зведеного загону направляються на вимогу КГП згідно з діючими наказами		**32 км**

Особливості оперативно-тактичної характеристики села Власівка:

Село розташовано на півдні Зіньківського району, праворуч траси Суми – Полтава по напрямку руху на Полтаву та на відстані 5 км від траси. Відстань до обласного центру – 85 км. Площа житлової забудови складає близько 700 га. Характер забудови – приватний сектор з 1- та 2-поверховими будинками. Поблизу загальноосвітньої школи (ЗОШ) розташовано 3-поверховий залізобетонний будинок на 2 під'їзди.

Дороги в центральній частині села, а також проїзди до птахофабрики (ПТФ), тваринницької ферми (ТФ) та насосної асфальтовані, інші дороги – ґрунтові.

Зовнішнє протипожежне водопостачання забезпечується від 6 ПГ, які встановлені на водопровідній кільцевій мережі діаметром 150 мм, з постійним тиском 2 атм. Для підйому тиску в мережі є насосна станція. У нічну годину (з 00:00 до 06:00) насосна не працює. Ввімкнення насосів здійснюється черговим насосної станції ((8241) 44 88). А також у центрі села заходиться водонапірна вежа, яка пристосована для забору води.

Продовження додатка 4

Схема села Власівка

Продовження додатка 4

Аркуш
корегування та відпрацювання оперативної картки

З яким караулом (зміною) відпрацьовано, ким відкореговано ОК (прізвище)			
1 караул (зміна)	2 караул (зміна)	3 караул (зміна)	4 караул (зміна)
1	2	3	4
	01.01.2025 Корегування ІВАНЕНКО		
02.01.2025 Відпрацьовано ПЕТРЕНКО	03.01.2025 Відпрацьовано БОБРИКА	04.01.2025 Відпрацьовано ЗАВІРЮХА	05.01.2025 Відпрацьовано КАПІТАНОВ
		01.01.2030 Коригування ЗАВІРЮХА	

Додаток 5
до Методичних рекомендацій із складання, корегування та відпрацювання оперативних карток гасіння пожеж
(пункт 5.5 розділу II)

УМОВНІ ПОЗНАЧЕННЯ ТА ЗНАКИ

1-4, П, Д

– сходова клітина з першого по четвертий поверх, вхід у підвал та на дах (позначається 1-4 (П, Д));

– вхід (вихід) у будівлю;

– ліфт;

– вихід на дах;

– слухове вікно, люк димовидалення;

– зовнішня пожежна драбина;

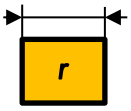

– генератор електричної енергії;

– акумуляторна батарея;

– місце відключення електропостачання будівлі з напругою 220 (380) і більше вольт;

– місце перекриття потоку природного газу в будівлю;

– місце перекриття потоку води у будівлю;

Аміак

– місце перекриття специфічної рідини (газу);

– місце встановлення фотоелектричної панелі або місце встановлення електричної батареї;

– у цьому місці існує механічна небезпека;

– трансформаторна підстанція;

– газорозподільна підстанція;

– заїзд на територію, який завжди відчинений;

– заїзд на територію, який може бути зачинений;

Продовження додатка 5

2 **4600**	–	поверховість / площа поверху;
	–	пульт управління;
	–	місце зовнішнього живлення пожежних кранів;
	–	місце зовнішнього живлення системи спринклерного пожежогасіння будівлі;
	–	місце зовнішнього живлення системи спринклерного пожежогасіння і пожежних кранів будівлі;
	–	насос-підвищувач;
	–	протипожежна стіна;
	–	люди у нічний час;
	–	особи з інвалідністю;
Аміак **1,8 т**	–	небезпечна речовина (хімічна, отруйна, вибухова, радіоактивна тощо);
П(М)У **120**	–	первинне (мобільне) укриття (120 – місткість, осіб);
НУ **О(В)120**	–	найпростіше укриття (О – окремо стояче; В – вбудоване; 120 – місткість, осіб);
ПРУ **О(В)120**	–	протирадіаційне укриття (О – окремо стояче; В – вбудоване; 120 – місткість осіб);
КТ	–	шахти, тунелі прокладання силових кабелів;
ІТІ	–	інформаційно-технологічна інфраструктура (шахти, тунелі прокладання електронних комунікаційних систем (лінії зв’язку, волоконно-оптичні кабелі));
ЦОД	–	приміщення центру обробки даних
СК	–	серверні кімнати
	–	місце зберігання речовин, гасіння яких не можна проводити водою

Додаток 6
до Методичних рекомендацій із складання, корегування та відпрацювання оперативних карток гасіння пожеж
(пункт 1 розділу III)

ЗАТВЕРДЖУЮ

_____
(посада, спеціальне звання,

_____
підпис, власне Ім’я та ПРІЗВИЩЕ)

ПЛАН-ГРАФІК
корегування оперативних карток гасіння пожеж на об’єкти та села, розташовані в районі виїзду

_____
(найменування державного пожежно-рятувального підрозділу,

_____
державного пожежно-рятувального загону, територіального органу ДСНС)

на 202__ рік

№ з/п	Найменування об’єкта (села), на який корегується ОК	Адреса об’єкта	Номер (ранг) направлення сил і засобів	Дата корегування	Посада посадової особи, яка корегує ОК	власне Ім’я та ПРІЗВИЩЕ посадової особи, яка корегує ОК	Відмітка про виконання
1							
2							

_____ (посада) _____ (підпис) _____ (Власне ім’я та ПРІЗВИЩЕ)

_____

Додаток 7
до Методичних рекомендацій із складання, корегування та відпрацювання оперативних карток гасіння пожеж
(пункт 5 розділу IV)

ЗАТВЕРДЖУЮ

_____
(посада, спеціальне звання,

_____
підпис, власне Ім’я та ПРІЗВИЩЕ)

ПЛАН-ГРАФІК
відпрацювання оперативних карток гасіння пожеж на об’єкти та села, розташовані в районі виїзду

_____
(найменування державного пожежно-рятувального підрозділу,

_____
державного пожежно-рятувального загону, територіального органу ДСНС)

на 202__ – 202__ роки

№ з/п	Найменування об’єкта, населеного пункту	Адреса	Номер (ранг) направлення сил і засобів	Місяць, на який заплановано відпрацювання ОК	ПІБ посадової особи, яка відпрацювала ОК	Дата відпрацювання	Теоретично / практично	Підпис
1								
2								

_____ (посада) _____ (підпис) _____ (Власне ім’я ПРІЗВИЩЕ)

_____